PROVINCIA

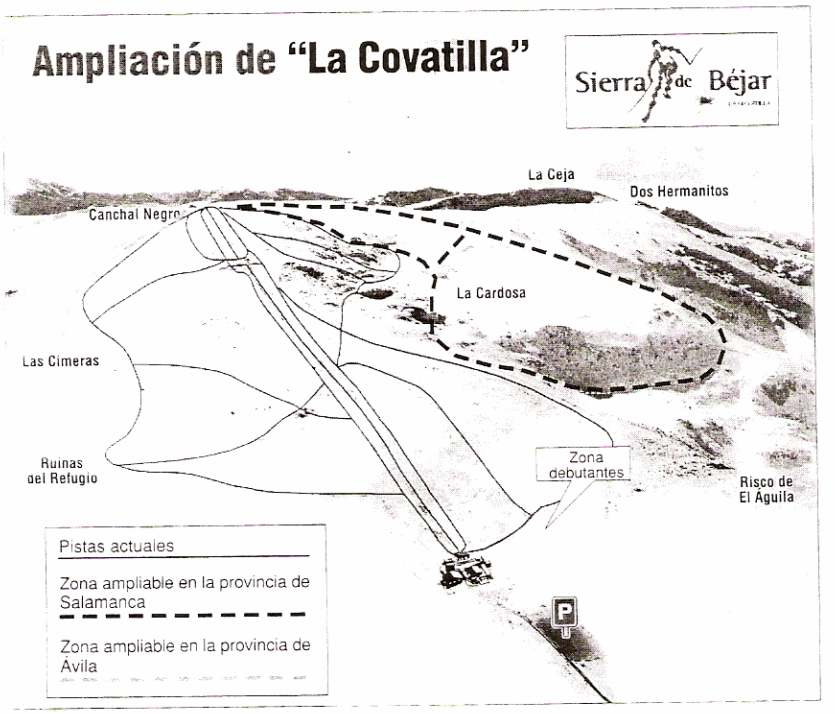

SIERRA DE BÉJAR ▮ ESQUÍ

La ampliación de la estación hacia Ávila podría contar con el respaldo de su Diputación

▮ Su presidente, Agustín González, ha asegurado que "La Covatilla merece su máxima ampliación por ser un punto estratégico"

TEL/E.F.M./T.B.B.

"La Covatilla merece su máxima ampliación por ser un punto estratégico del norte de Extremadura, Castilla y León y Portugal", ha asegurado el presidente de la Diputación Provincial de Ávila, Agustín González, dando a entender de este modo su apoyo a la ampliación de la estación de esquí Sierra de Béjar, prevista en su Plan Director y que podría incluso traspasar los límites provinciales de Salamanca.

González, que también es alcalde de El Barco de Ávila, localidad ribereña del Tormes ubicada en el valle donde se unen las sierras de Gredos y Béjar, aseguró a LA GACETA que la posible ampliación de las pistas a la vertiente abulense se trataría de un proyecto "de viabilidad provincial que habría que apoyar". Si bien, no ha detallado aún el nivel de compromiso adquirido con la empresa gestora de las actuales instalaciones, Gecobesa, que ya ha iniciado gestiones o contactos en la localidad abulense de El Tremedal, en el término de Solana de Ávila, para valorar la posibilidad de adquirir terrenos en la zona del Canchal Negro.

Según continuó Agustín González, "es necesario explotar al máximo la sierra en las dos laderas, aunque con el máximo rigor", lo que da a entender el apoyo del presidente provincial a una posible ampliación respetando el entorno, que se encuentra en el entorno más próximo del Parque Regional de Gredos. En este sentido, fuentes próximas a la estación de esquí han señalado que se trata de una situación "complicada" que retrasa los proyectos ya que cualquier modificación que se haga debe contar, por mínima que sea, con su Declaración de Impacto Ambiental. Sin embargo, las mismas fuentes señalan que la zona sería óptima para la práctica del esquí y que en cuestión de infraestructuras viarias no habría grandes compliaciones, ya que la carretera de El Tremedal se encuentra a un kilómetro y medio de lo que sería el final de una de las pistas de la Sierra del Chorrito. De todos modos, desde la estación de esquí se recuerda que son los ayuntamientos y los propietarios "los que tienen que pelear" en caso de que consideren oportuno dicho proyecto. El presidente de su Diputación ya ha demostrado su voluntad.

EL DETALLE

Solana de Béjar, hasta 1979. Aunque no hay ningún proyecto concreto ni público de ampliación hacia Ávila, la zona de El Tremedal guarda una estrecha relación con la sierra y la comarca de Béjar. De hecho, formó parte de la tierra de Béjar hasta que en



Imagen del Canchal Negro./TEL

1833 pasó a la provincia de Ávila. Además, El Tremedal se fusionó con la localidad de Solana de Béjar en 1977 y que dos años después cambió su nombre por el de Solana de Ávila. Además, la parte superior de la estación, el Canchal Negro, sirve también de límite con el municipio de Solana.



Imagen de la quinta temporada de la estación de esquí./FOTOS: TEL



Vista de El Barco de Ávila con la ladera abulense de la Sierra de Béjar al fon

Antecedente de San Glorio

Aunque la ampliación de la estación de esquí en el entorno del Parque de Gredos es complicada, en Béjar no se pierde toda esperanza gracias al reciente antecedente de la estación de esquí de San Glorio, donde la Junta ha modificado el Plan de Ordenación de los Recursos Naturales del Parque Natural de Fuentes Carrionas y Fuente Cobre-Montaña Palentina. La decisión fue tomada por el Consejo de Gobierno de la Junta de Castilla y León del pasado 9 de marzo como consecuencia de la solic planteada por varios ayu mientos de la zona y las pro Cortes regionales para mo car la normativa que impi desarrollo de los proyectos d taciones de esquí alpino, s pre que existan garantías de servar el patrimonio natura similitud es mayor cuando s serva que San Glorio divid terrenos entre las provinci León, Palencia y Cantabria.